UNIVERSIDAD NACIONAL DE BARRANCA

CÁTEDRA UNAB

Historia de Barranca

Mg. Cristina Pilar Damián Espinoza

Barranca
inolvidable

MERCADO ANTIGUO.
BARRANCA

Antiguo tren cañero!!! Paramonga años 20!!!

Pativilca

Paramonga
Ancash
Pativilca
Barranca
Supe Puerto
Supe
Huaura

CIRCUITO TURISTICO – PROVINCIA DE BARRANCA-LIMA-PERU

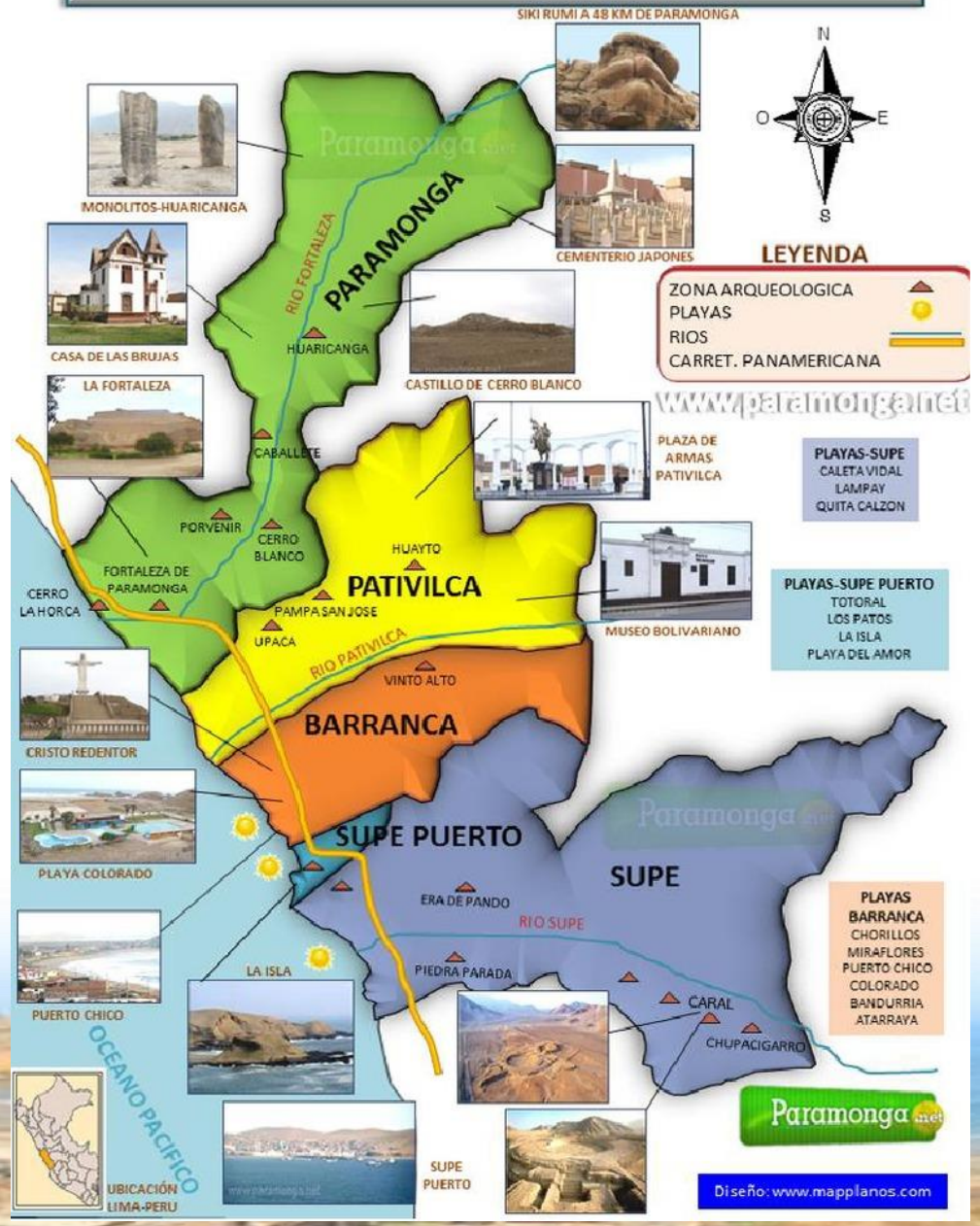

ORIGENES

- Sus orígenes se remotan al preincaica con su antiguo nombre (**GUAMANMAYO**) que en quechua significa **“Gavilán de Rio”**. Sobre el particular, el cronista español **Pedro de Cieza de León**, a su paso por la localidad de Barranca en 1,547, dijo “Valle de Guamán que en castellano quiere decir “Rio del Halcón”.

- Según versión del gobernador español **Cristóbal Vaca de Castro** en 1543, nos señala que la antigua Barranca estuvo situada entre los fundos de "El Potao" y el "El Molino" y que fueron los antiguos pobladores quienes bautizaron a nuestra zona con el nombre de Barranca, probablemente por la existencia de numerosas barrancas que descuelgan sobre las riberas del río Pativilca.

- Nuestra provincia en el pasado, fue área de influencia de muchas culturas a lo largo de su historia, desde el periodo lítico por la cultura Chavín, el imperio Wari, y del reino Chimú, quienes hacían pagar tributos en oro, plata, cobre y piedras preciosas a sus antiguos pobladores.

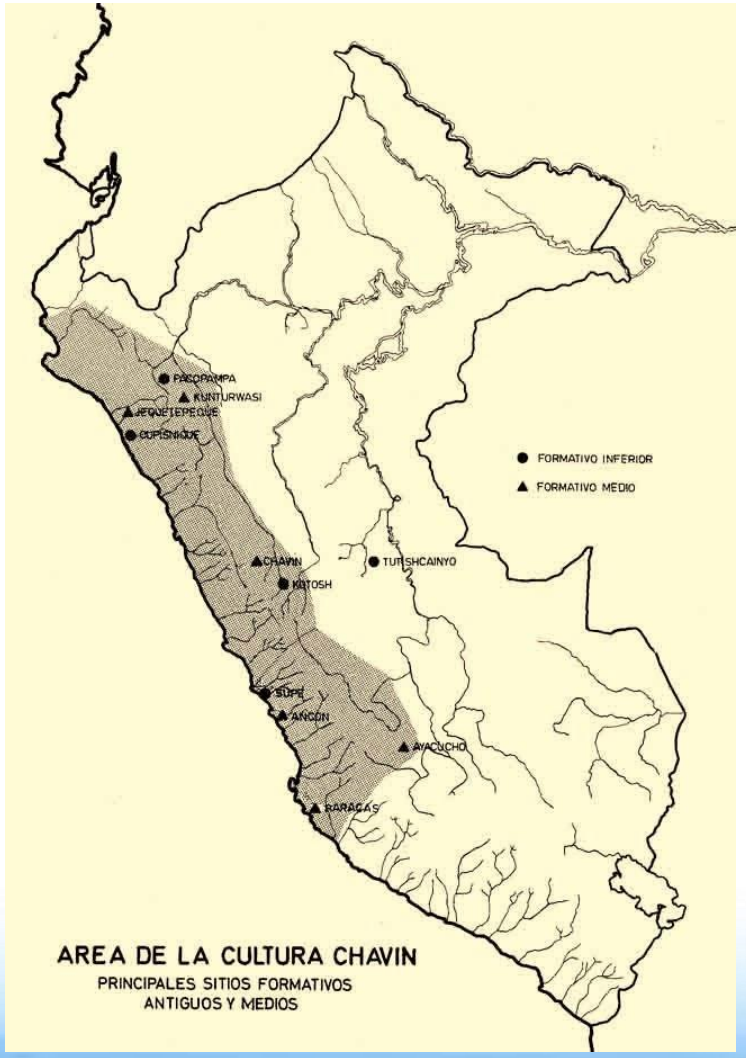

En el año 1500 de nuestra era, nuestro territorio estaba ocupado básicamente por estos pueblos:

a) El gran Chimú, que se extendía desde la costa norte en Tumbes, hasta lo que hoy es Paramonga, por el sur.

b) El Reino de Pachacamac, cuyo centro estaba en Lima y tenía como tributarios a los pequeños señoríos de Chancay, Huaura y Barranca.



c) El reino de Chincha, comprendía los territorios de Lunahuaná, de Hurcu, Mala, Quilca, en la costa sur.

Fue el inca **Pachacútec** quien organizó un poderoso ejército, de 100,000 hombres aproximadamente, bajo el mando de su hermano Cápac Yupanqui, quien inició la invasión por el sur con el fin de conquistar a los tres reinos. Sometidos estos, bajo el dominio de los quechuas, pasaron a formar parte del imperio incaico.

Todo esto sucedió unos cincuenta o sesenta años antes de la llegada de los españoles al Perú, aproximadamente a fines del siglo XV e inicios del siglo XVI.

Después con la colonización de los españoles, los nuevos inmigrantes deciden construir un nuevo centro poblado mas cerca a la costa, exactamente la Plaza de Armas de Barranca. Ellos fundan una Iglesia a la cual denominan San Ildefonso, y para poder distinguirla de otra iglesia en la sierra con el mismo nombre, deciden inscribirla como "Iglesia San Ildefonso de las Barrancas", básicamente por los barrancos que rodean por el rio Pativilca y la costa al océano.

- Otros investigadores manifiestan que después de un **Terremoto** en donde se caen las casa de la zona de Molino, es que la población se muda hacia el nuevo centro de Barranca. Lo que ahora es la plaza de armas y definitivamente adquiere importancia primordial cuando en los años 1930, el presidente **Benavides** ejecuta la obra de la carretera panamericana desde Tumbes hacia Tacna, lo cual asienta el comercio de la zona sobre la avenida Gálvez.

LIMITES

- Limita por el norte con las provincias ancashinas de Huarmey y Bolognesi, por el este con la provincia de Ocros, por el sur con la provincia de Huaura y por el oeste con el océano Pacífico.

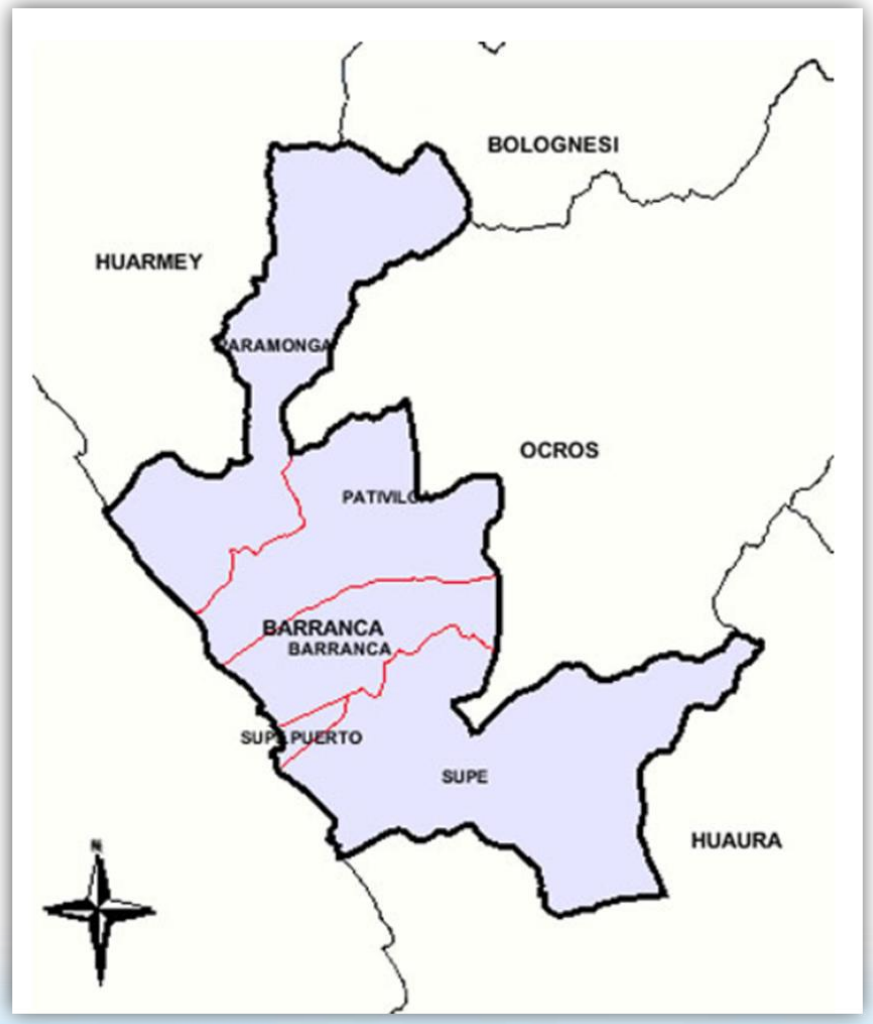

- Dentro de la **división eclesiástica** de la Iglesia católica del Perú, pertenece a la diócesis de Huacho.
- Se encuentra regulada **judicialmente** por el distrito judicial de Huaura

CREACIÓN POLÍTICA

- Barranca formaba parte de la antigua y extensa Provincia de Chancay (cuya capital era Huacho) hasta su creación política como provincia independiente.
- Barranca fue creada políticamente **como distrito en 1823**, siendo Pío Dávila su primer alcalde. Pasó a la categoría de **provincia** mediante la Ley n.º 23939, del **5 de octubre de 1984**, dada en el segundo gobierno del presidente Fernando Belaúnde Terry.

Extensión

- La provincia tiene una de 1355,87 km² y está dividida en 5 distritos:
    1. Barranca
    2. Paramonga
    3. Pativilca
    4. Supe
    5. Supe Puerto

- PLATOS TIPICOS
- ZONAS TURISTICAS
- MITOS Y LEYENDAS

- ¿Según el ultimo censo cual es la cantidad de habitantes en la provincia de Barranca?
- ¿Cuáles son las provincias que conforman el departamento de Lima en el Perú?
- ¿Investiga sobre el antiguo ferrocarril en Barranca?
- ¿La Corte Superior de Justicia de Huaura tiene jurisdicción sobre que provincias?
- La Diócesis de Huacho extiende su jurisdicción eclesiástica sobre cuales provincias?

ACTIVIDAD

- Realizar un resumen y comentario personal del siguiente articulo

https://www.infobae.com/peru/2025/01/14/la-casa-de-playa-de-jose-maria-arguedas-la-historia-de-un-predio-alquilado-comprado-por-un-familiar-y-declarado-monumento/